PLANIFICACIÓN TERRITORIAL Y ESTRATÉGICA PARA LA SEGURIDAD CIUDADANA

SESIÓN 4: LÓGICAS ESPACIALES, GEOTECNOLOGÍAS Y GESTIÓN DE LA DEMANDA

DEL CONTROL DEL DELITO A LA GESTIÓN DEL TERRITORIO

NotebookLM

SEGURIDAD PÚBLICA
(Enfoque Unicausal)

Estado-Céntrico
Reactivo
Policial

SEGURIDAD CIUDADANA
(Multicausal)

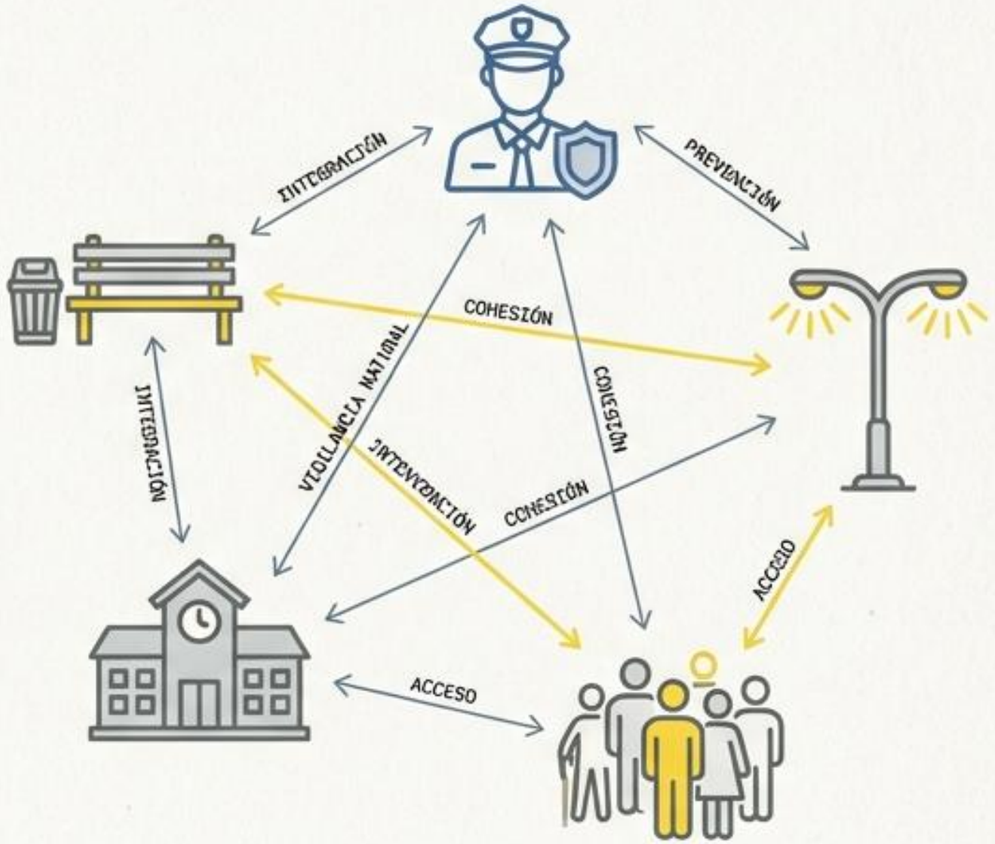

"La seguridad no es solo ausencia de delito. Es una condición derivada de la **convivencia** la **calidad del entorno urbano** (Slate Grey), y la **inclusión social** (Safety Yellow). (Lectura 8).

NotebookLM

La Realidad vs. La Percepción

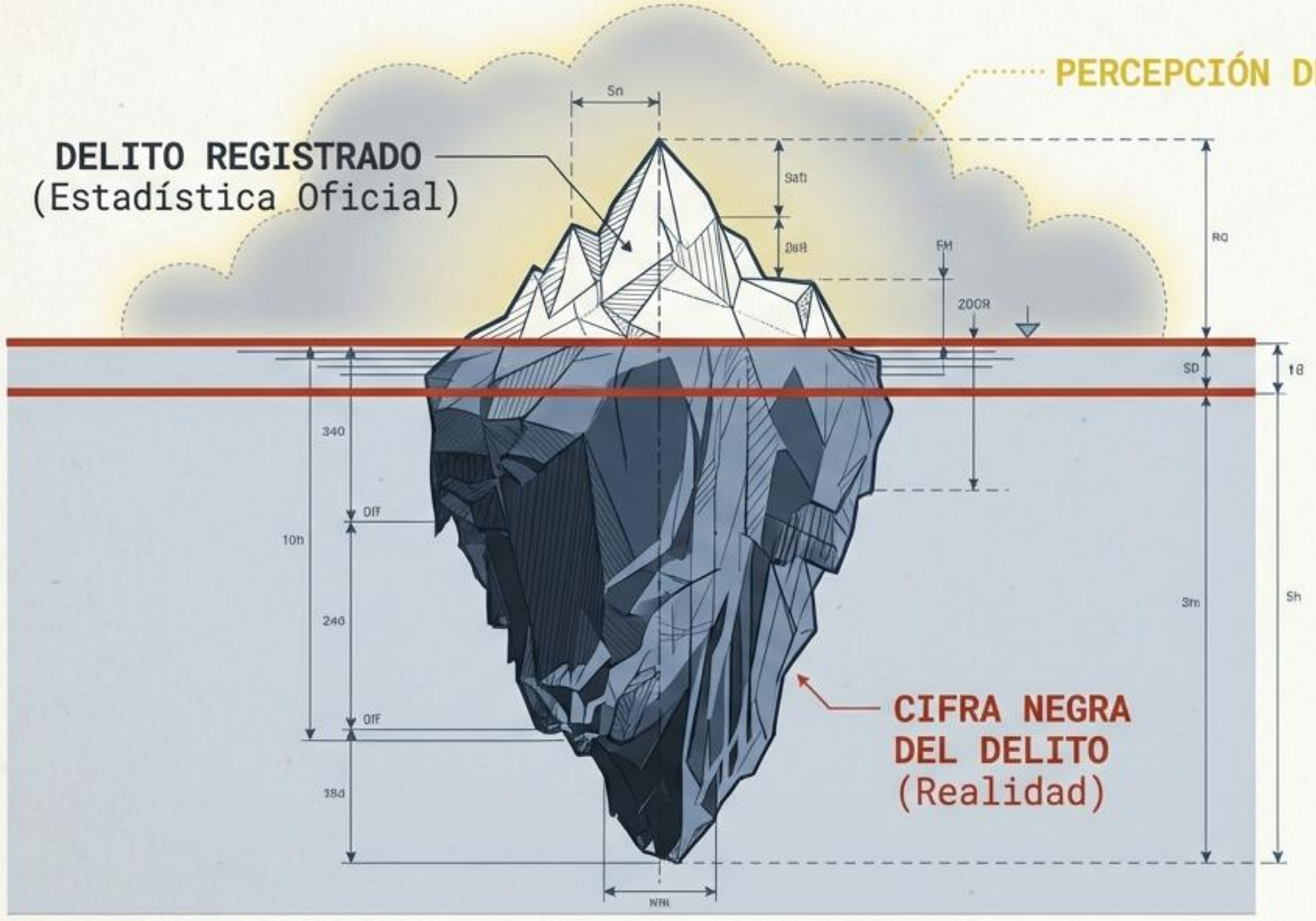

La ansiedad ciudadana no siempre correlaciona con la tasa real. El miedo detona cambios drásticos en el comportamiento urbano: aislamiento y abandono del espacio público.

NotebookLM

CASO DE ESTUDIO: COLONIA KENNEDY (TEGUCIGALPA)

La Paradoja de la Prevención Situacional

El ‘amurallamiento’ destruye la vigilancia natural. Al aislarse, el vecino pierde el control visual de la calle, convirtiendo el espacio público en tierra de nadie y aumentando el temor que intentaba mitigar.

NotebookLM

Provisión de Servicios Públicos y Orden Urbano

Teoría de las Ventanas Rotas (Contexto Latino)

- Mala iluminación reduce la vigilancia natural.
- La basura y el desorden elevan la ansiedad ciudadana.
- El deterioro físico facilita la ocurrencia del delito.

NotebookLM

Criminología Ambiental: Leyendo el Territorio

GENERADORES

Concentran masas. Oportunidad por aglomeración.

ATRACTORES

Lugares conocidos por ofensores. Búsqueda intencional.

ATRACTORES

Lugares conocidos por ofensores. Búsqueda intencional.

DETRACTORES

Vigilancia natural y cohesión social inhiben el crimen.

NotebookLM

Vitalidad Urbana vs. Sociabilidad Barrial (Lectura 2)

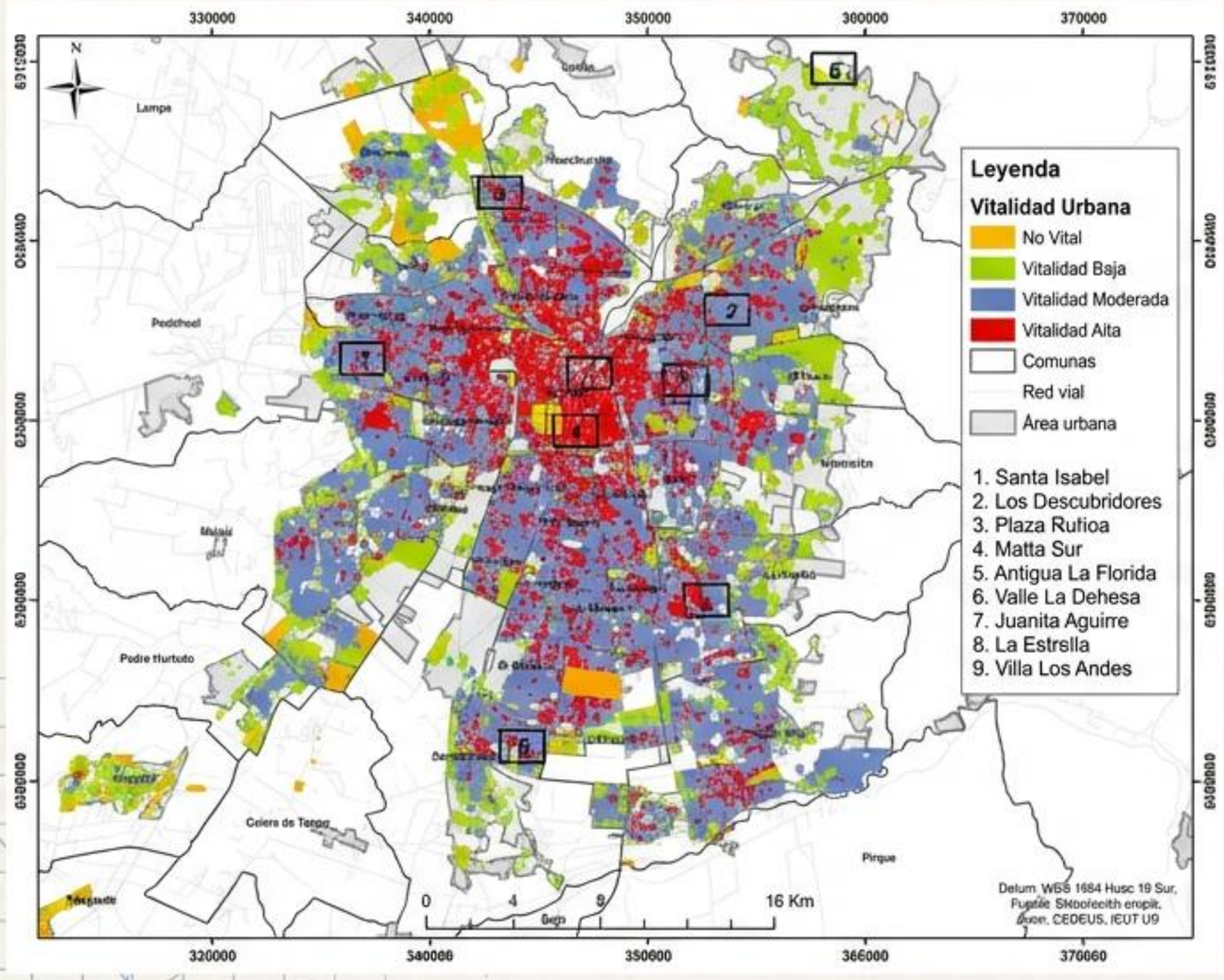

Densidad vs. Familiaridad Pública

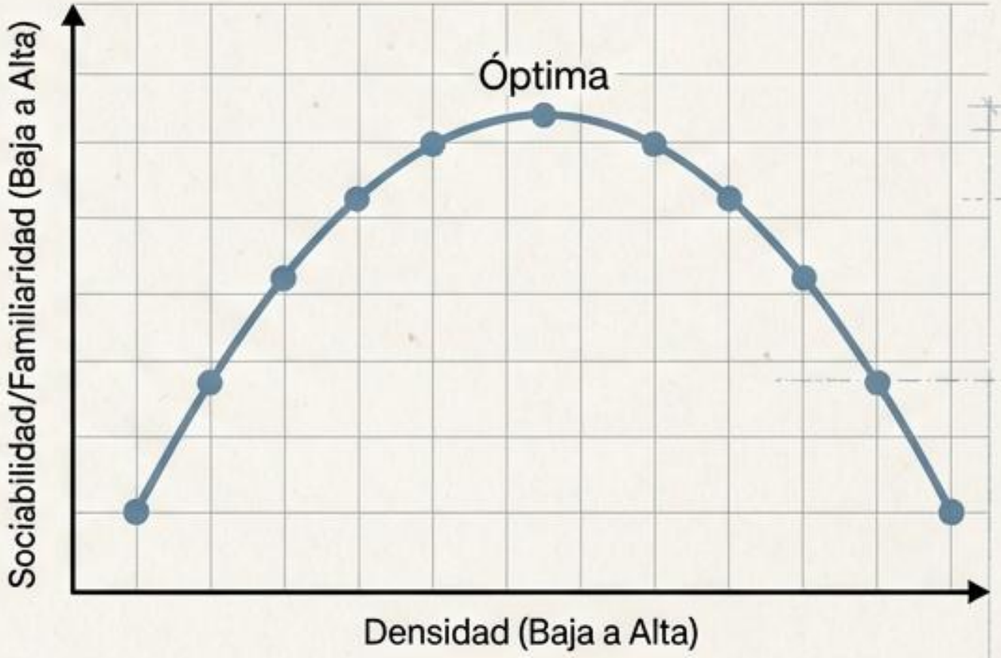

El Mito de Jane Jacobs en Latinoamérica:

La alta densidad (torres verticales) a menudo genera anonimato, no seguridad. La seguridad real depende de los vínculos vecinales, no solo del flujo de personas.

NotebookLM

Geomarketing Social: El Perfil del Territorio

User Profile

Variables de Cohesión

Permanencia Residencial
Años viviendo en el barrio = Mayor red de apoyo.

Composición del Hogar
Hogares con niños = Más uso del espacio público (Ojos en la calle).

Nivel Socioeconómico
Altos ingresos = Tendencia a la privatización y menor sociabilidad.

La planificación debe adaptarse al perfil sociodemográfico, no solo al físico.

NotebookLM

La Caja de Herramientas: Sintaxis Espacial



SISTEMA INTEGRADO (Predecible / Vigilancia Natural)

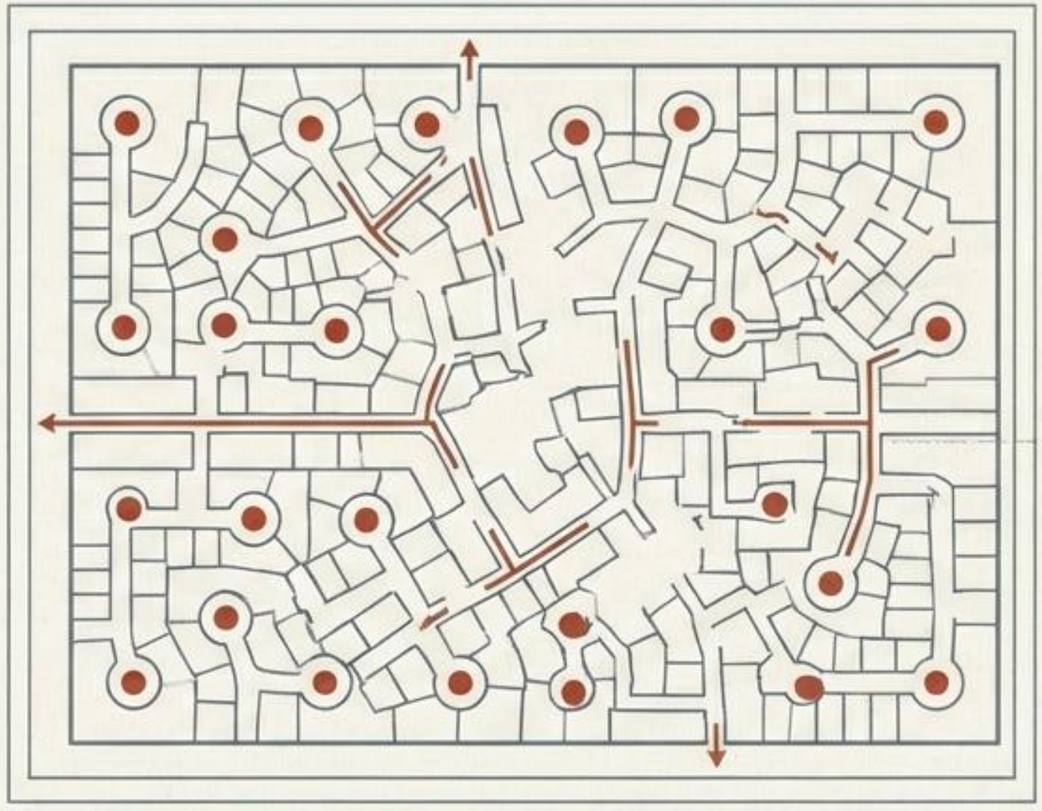

SISTEMA SEGREGADO (Misterioso / Vulnerable)

La configuración espacial determina el movimiento. El flujo de “extraños” no es una amenaza, es un recurso de vigilancia.

NotebookLM

Campos Visuales: Isovistas y Vigilancia

Para la seguridad, “Cuánto veo” (campo visual amplio) es más importante que “Cuánto me ven”. Las esquinas ciegas y muros altos generan ansiedad.

NotebookLM

Geotecnologías y Modelado Espacial

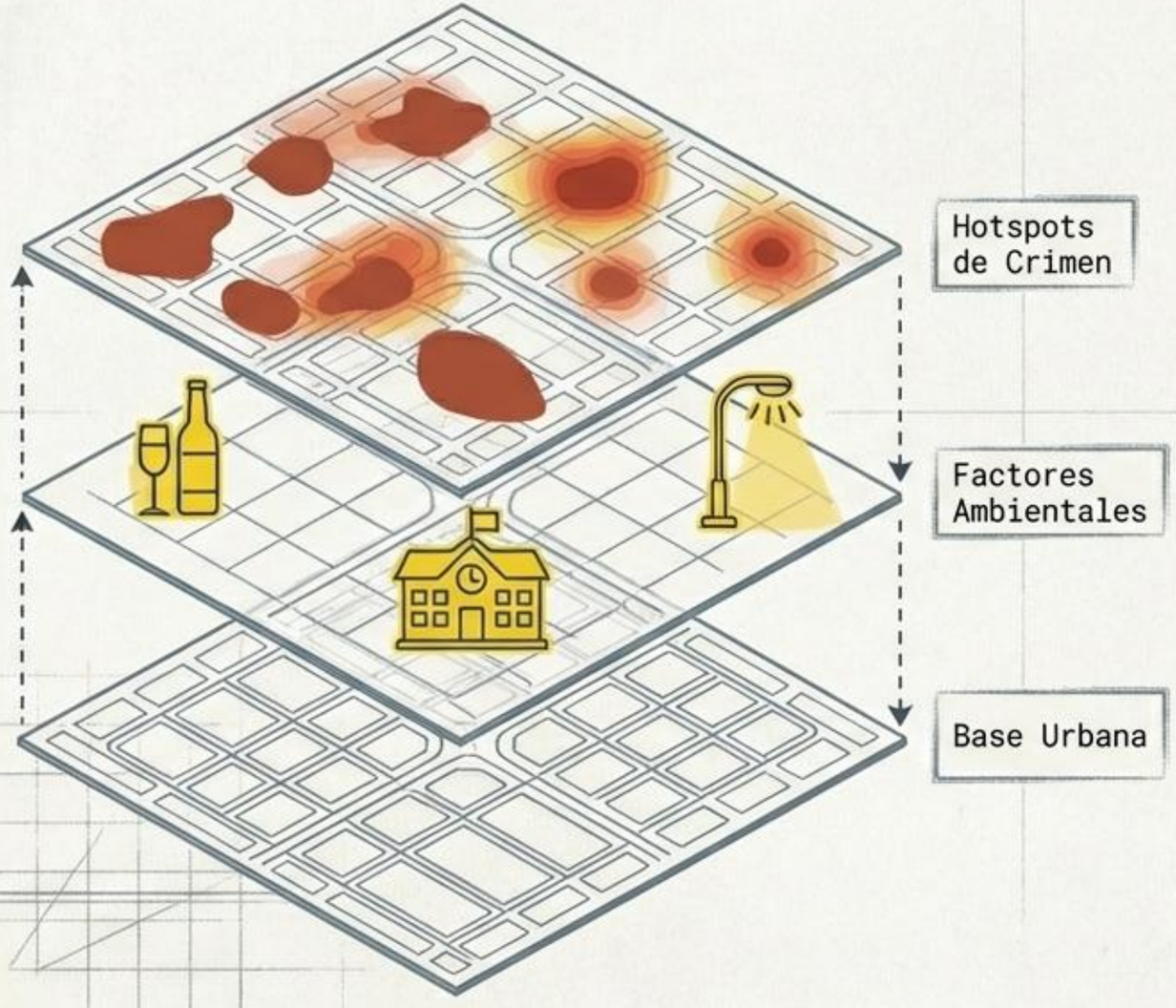

Econometría Espacial

Análisis de la Autocorrelación Espacial. El delito no ocurre en el vacío; existe un “efecto contagio” entre zonas vecinas.

NotebookLM

La Logística de los Mercados Ilegales

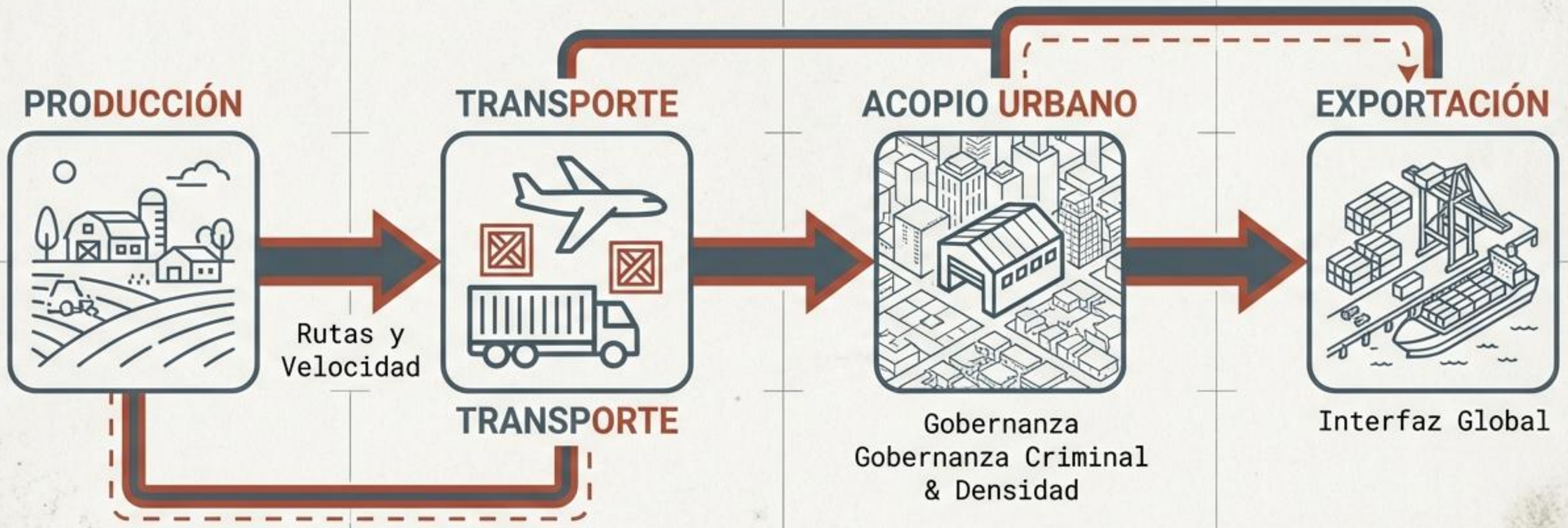

El crimen organizado utiliza planificación territorial racional para maximizar beneficios y minimizar riesgos.

NotebookLM

Modelando la Toma de Decisiones Criminal

DECISION MATRIX

MAXIMIZACIÓN DE BENEFICIOS

- Basado en costos monetarios y pérdidas.
- Eficiencia económica.

DECISION MATRIX

?

MAXIMIZACIÓN DE SUMINISTRO

- Objetivo: Saturar el mercado.
- Prioriza volumen sobre costo. Minimizar fricción.

INTERVENTION FORECAST

Entender el modelo permite predecir el “efecto desplazamiento” ante la intervención policial.

NotebookLM

Planificación Estratégica: Los 3 Tipos de Demanda

DEMANDA REACTIVA

Respuesta a incidentes (911).

DEMANDA PROTECTORA

Patrullaje preventivo, inteligencia, anticipación.

DEMANDA INTERNA

Procesos administrativos y burocracia.

FAILURE DEMANDA

External: Errors lead to extra demand outside of the organisation, e.g. additional public demand or protective demand.

Internal: Errors lead to extra demand within the organisation, e.g. additional administrative efforts necessary to compensate.

NotebookLM

La Carga Oculta: Demanda por Falla

DEMANDA POR FALLA: Trabajo generado por no resolver el problema correctamente la primera vez.

- **Falla Externa:** Llamada ignorada.
- **Falla Interna:** Burocracia redundante.

NotebookLM

Sistema Complejo Adaptativo

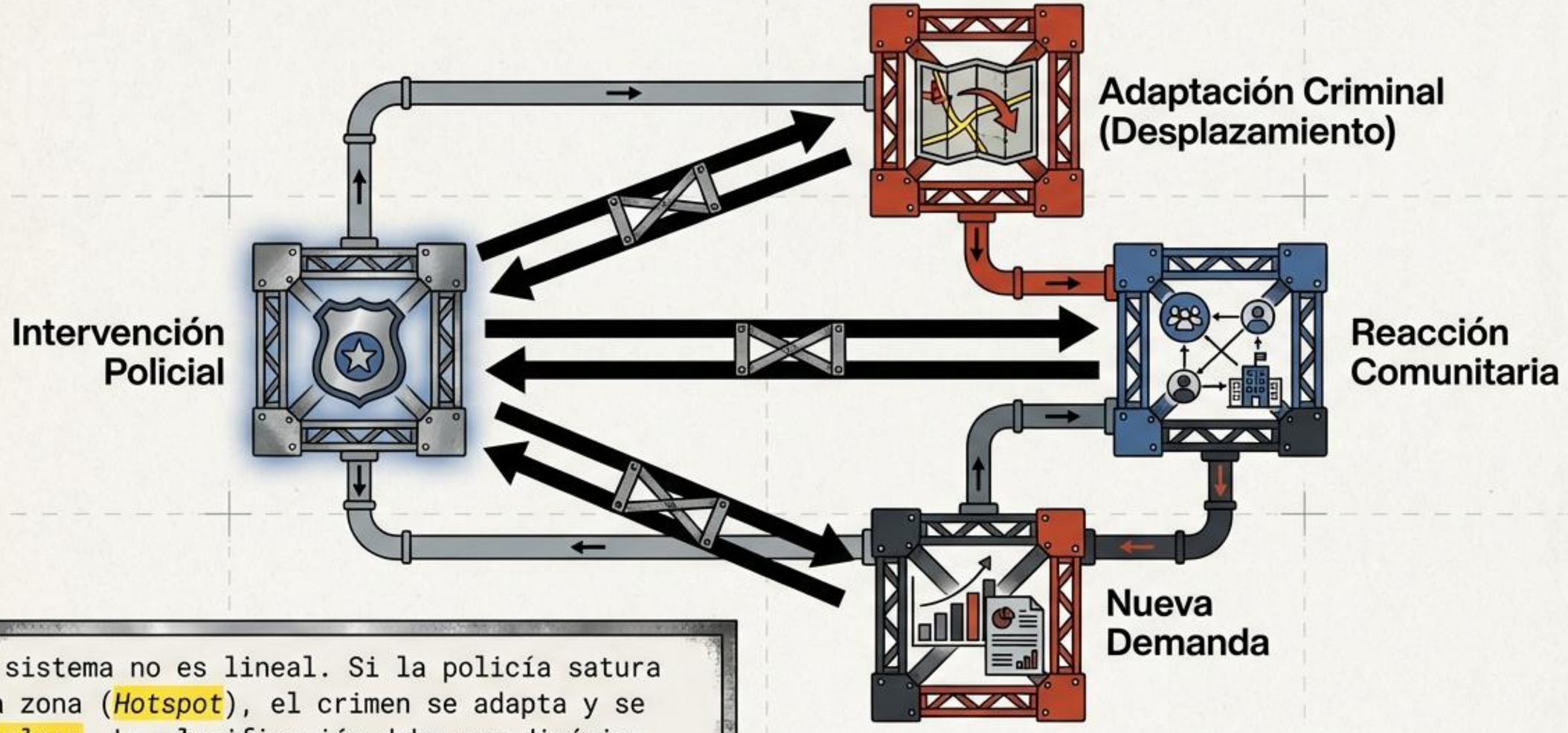

El sistema no es lineal. Si la policía satura una zona (*Hotspot*), el crimen se adapta y se desplaza. La planificación debe ser dinámica.

NotebookLM

Localización Óptima de Recursos

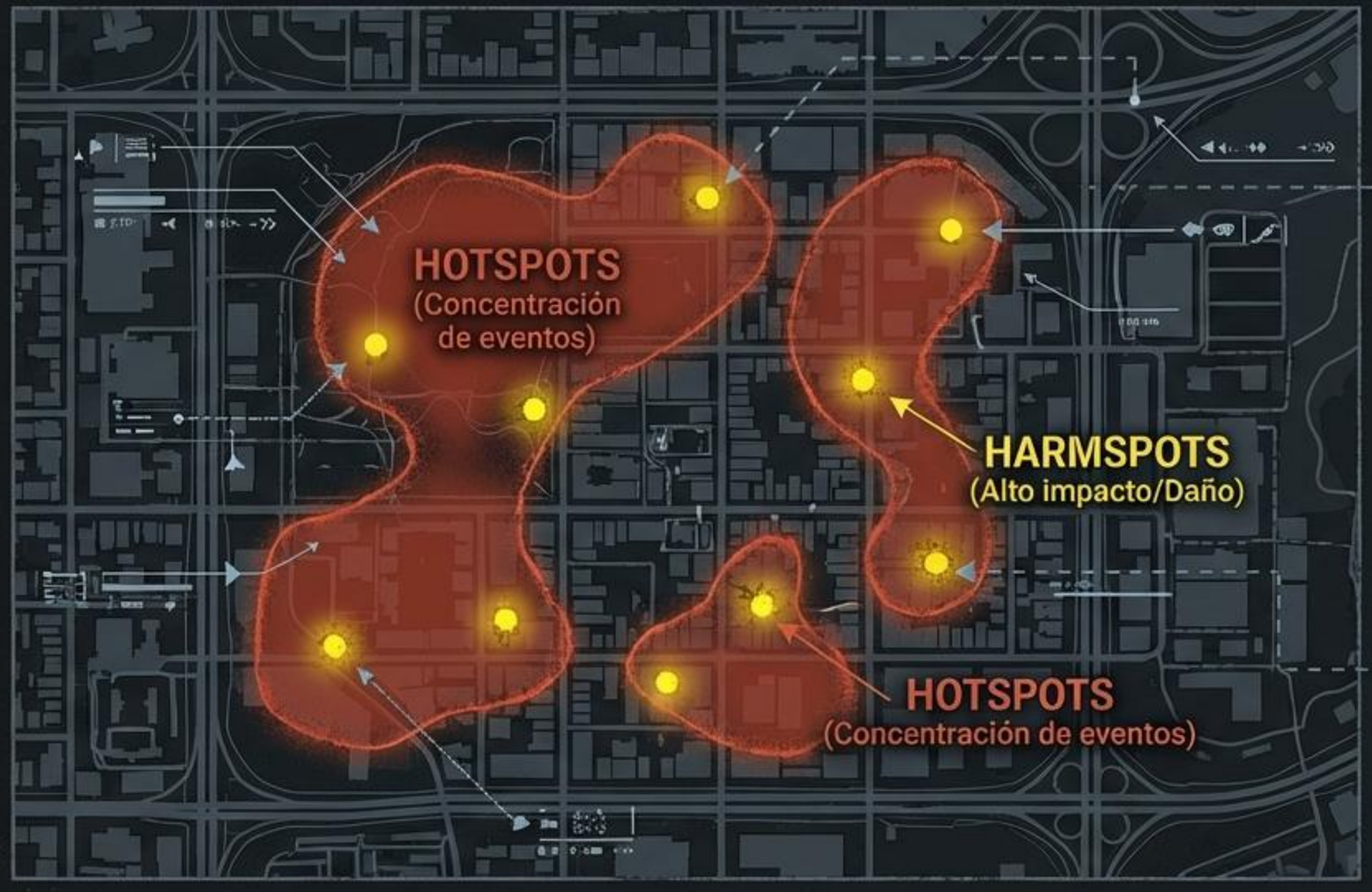

Enfoque Orientado a Problemas:

- Si es Generador: Vigilancia y diseño.
- Si es Atractor: Inteligencia y desarticulación.
- Asignar recursos según el tipo de demanda específica del territorio.

NotebookLM

Asistencia Social vs. Control Policial



Demanda Social
(Ruidos, Salud Mental, Situación de Calle)

Respuesta Policial
(Ineficiente para estos casos)

Canalizar la demanda social hacia servicios especializados libera recursos policiales para el crimen real y reduce la Demanda por Falla.

NotebookLM

Síntesis: El Ciclo de Planificación Territorial

1. DIAGNÓSTICO

Roboto Mono
Percepción •
Cifra Negra •
Perfil Social •

3. INTERVENCIÓN

Roboto Mono
• Gestión de Demanda
• Localización Óptima
• Diseño

2. ANÁLISIS

Geotecnologías •
Sintaxis Espacial •
Logística Criminal •

2. ANÁLISIS

• Geotecnologías
• Sintaxis Espacial
• Logística Criminal

NotebookLM

Conclusiones

- El territorio es una **variable activa**: facilita o inhibe el crimen.
- El **“amurallamiento”** genera **más inseguridad** (Paradoja de Kennedy).
- Transición de **“Demanda Reactiva”** a **“Demanda Protectora”**.
- La planificación requiere **datos de calidad** para reducir la incertidumbre.

NotebookLM